Omni
歐米智聯

雲端管理平台

操作手冊

第一步驟 登入網頁

網頁資料

網址:https://s2.geonerve-iot.com/home.php

帳號: 忘記帳密 請洽廠商協助

密碼:

第二步驟 進入網頁

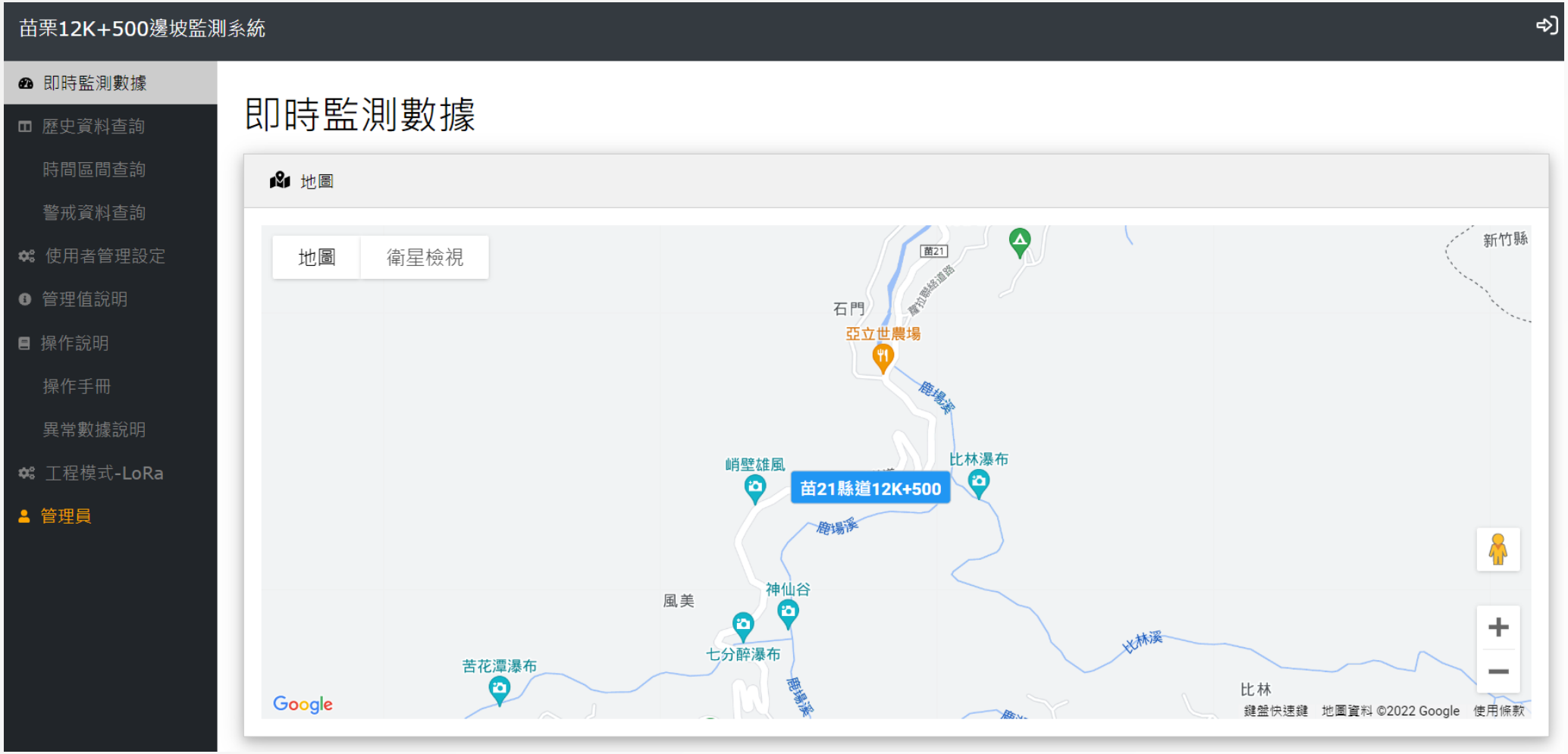
苗栗12K+500邊坡監測系統
即時監測數據
歷史資料查詢
時間區間查詢
警戒資料查詢
使用者管理設定
管理值說明
操作說明
操作手冊
異常數據說明
工程模式-LoRa
管理員
即時監測數據
地圖
地圖
衛星檢視
新竹縣
石門
亞立世農場
鹿場溪
峭壁雄風
苗21縣道12K+500
比林瀑布
鹿場溪
風美
神仙谷
七分醉瀑布
苦花潭瀑布
比林溪
比林
Google
鍵盤快速鍵　地圖資料 ©2022 Google　使用條款

第三步驟 點選大圖釘

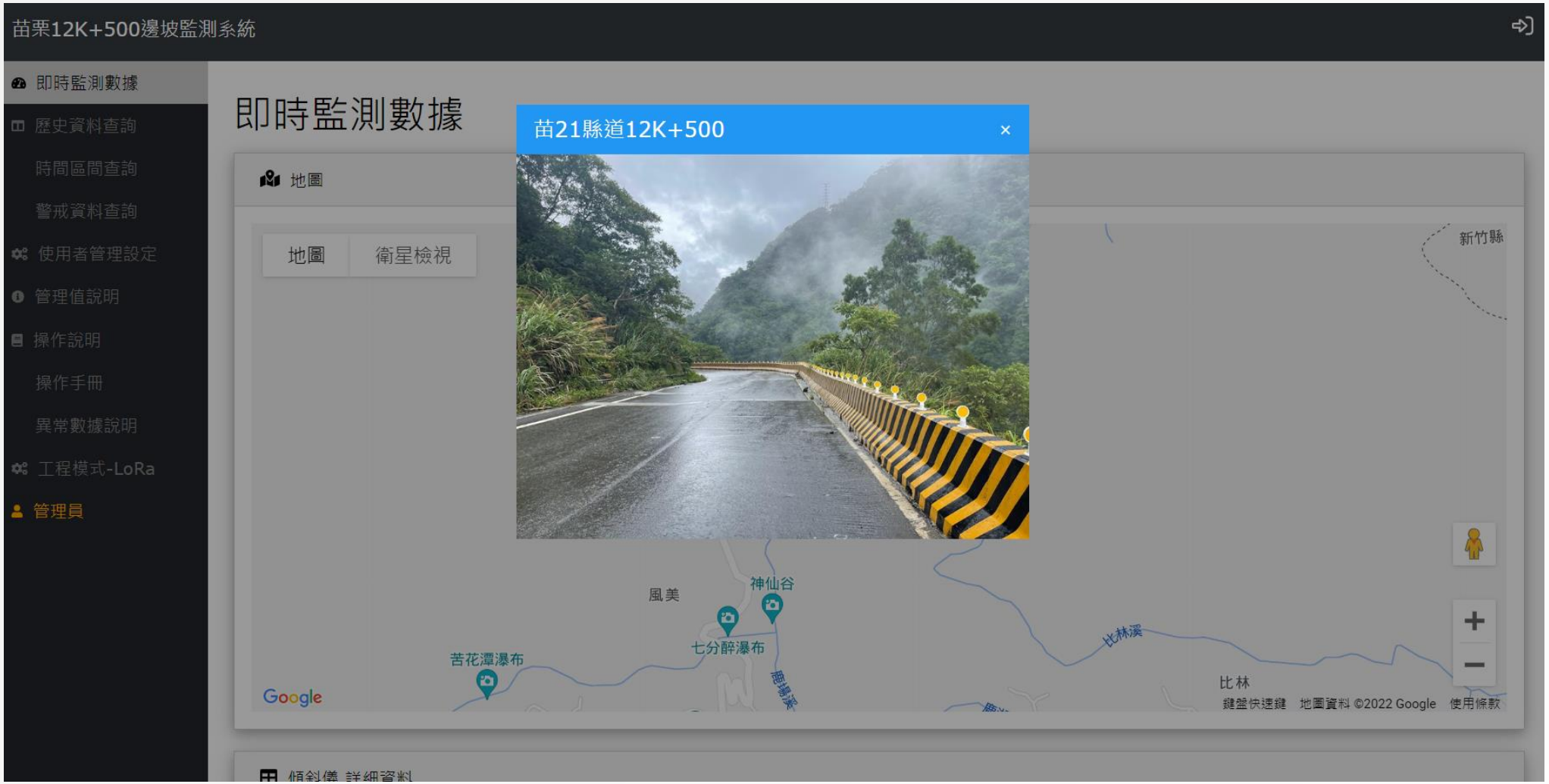
苗栗12K+500邊坡監測系統
即時監測數據
歷史資料查詢
時間區間查詢
警戒資料查詢
使用者管理設定
管理值說明
操作說明
操作手冊
異常數據說明
工程模式-LoRa
管理員
即時監測數據
地圖
地圖
衛星檢視
苗21縣道12K+500
新竹縣
風美
神仙谷
七分醉瀑布
苦花潭瀑布
比林溪
比林
鍵盤快速鍵
地圖資料 ©2022 Google
使用條款
Google

第四步驟 觀看即時監測數據

歷史資料

點擊歷史資料查詢>點擊時間區間>選擇設備>開始時間>結束時間>點擊查詢

歷史資料

接著拉到頁面最底下 點擊下載

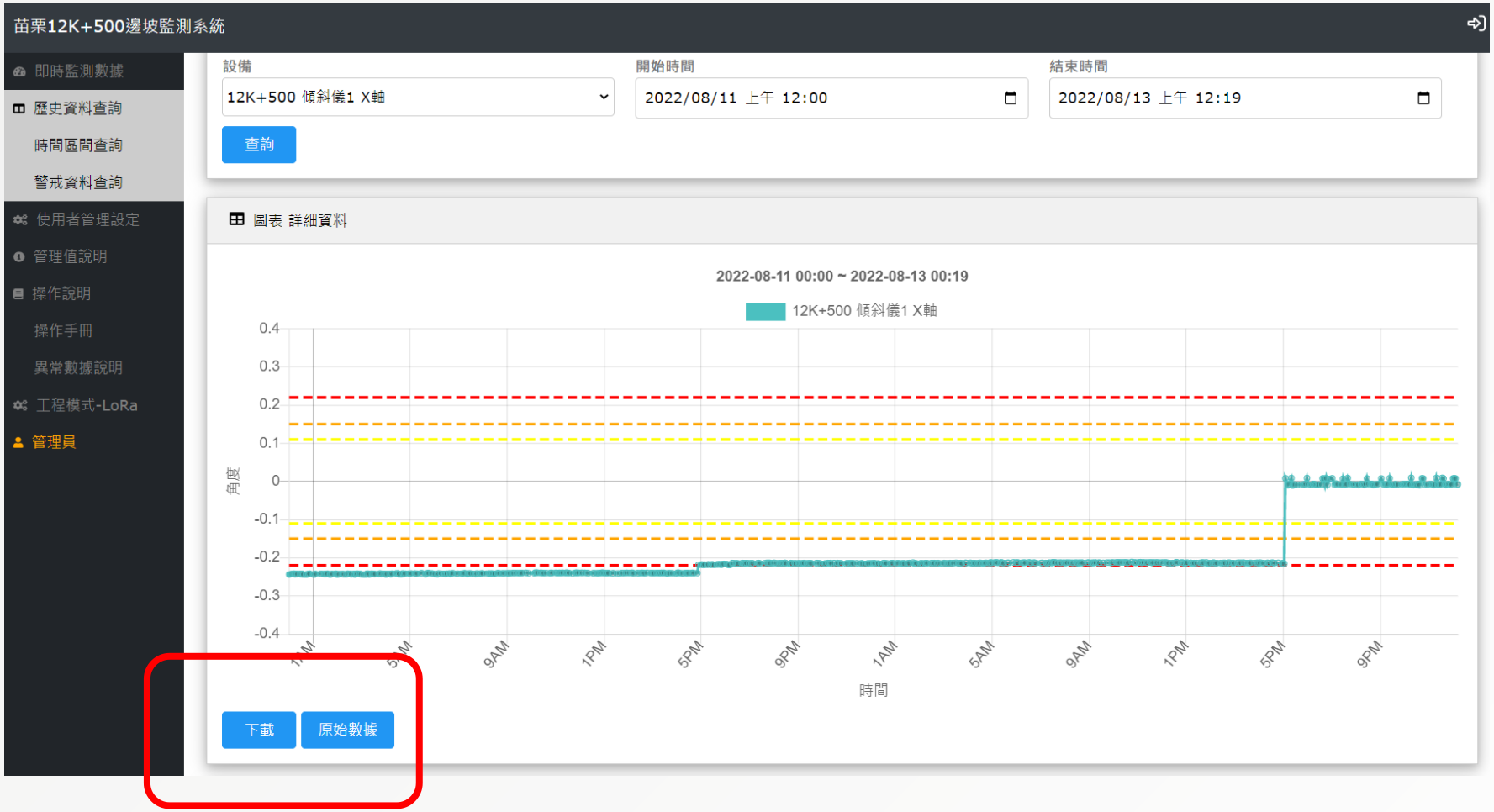

使用者管理設定

點擊使用者設定>點擊新增>點擊新增

使用者管理設定

輸入帳號、密碼與名稱

管理值說明

苗栗12K+500邊坡監測系統
即時監測數據
歷史資料查詢
時間區間查詢
警戒資料查詢
使用者管理設定
管理值說明
操作說明
操作手冊
異常數據說明
工程模式-LoRa
管理員
管理值說明
傾斜儀
燈號 綠 黃 橙 紅
狀態 正常 預警 警戒 行動
傾斜角度 - 0.11 度 0.15 度 0.22 度
雨量
燈號 綠 黃 橙 紅
狀態 正常 預警 警戒 行動
24小時累積雨量 - ≧ 300 mm ≧ 400 mm ≧ 500 mm
Copyright © 2022 歐米智聯股份有限公司

網　頁　操　作

網頁通報

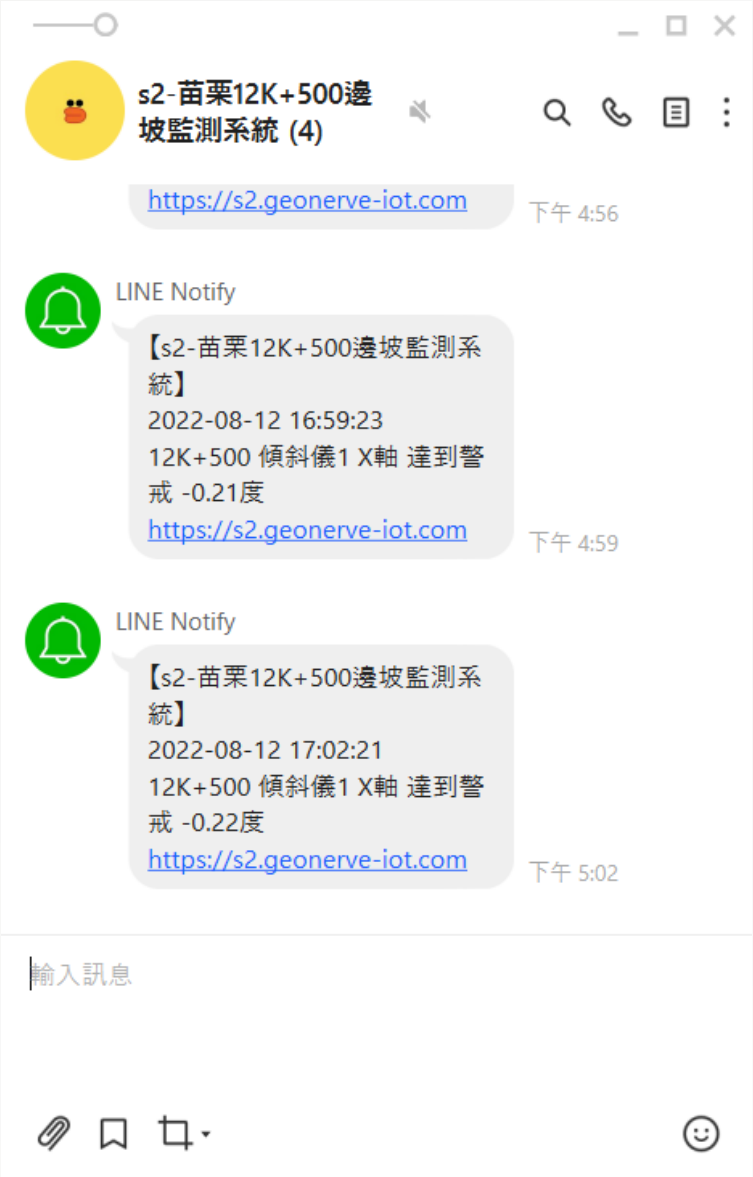
s2-苗栗12K+500邊坡監測系統 (4)
https://s2.geonerve-iot.com
下午 4:56
LINE Notify
【s2-苗栗12K+500邊坡監測系統】
2022-08-12 16:59:23
12K+500 傾斜儀1 X軸 達到警戒 -0.21度
https://s2.geonerve-iot.com
下午 4:59
LINE Notify
【s2-苗栗12K+500邊坡監測系統】
2022-08-12 17:02:21
12K+500 傾斜儀1 X軸 達到警戒 -0.22度
https://s2.geonerve-iot.com
下午 5:02
輸入訊息